Nederlandse Jeugdbond voor Natuurstudie

WAARNEMINGSFORMULIER

Bokkingshang 1, 7411 GG Deventer



gebied (3)

terrein, gemeente	situatieschets of andere opmerkingen
coördinaten	1,9,6 WO 4,2,1 OW
datum	1,1,-,0,7,-,8,9
onderwerp	RCC
gelegenheid	
temperatuur	
bewolking	
neerslag	
zicht	
windricht./kr.	
korrespondentieadres	aanwezigen: Wiebe Borren, Hester de Boer, Reuwd Stolk, Matthijs Courbois, Willemijn ..., Carla Arend, Frederiek de Heer.



Fysisch	breedte	25-30 cm
	diepte	2,5 m
	bodem	beton, stenen
	water	helder.
	watertemp.	aangenaam, niet warm of koud, je voelt alleen natte/gheid
	stroomsnelheid	0,16 m/s
	oevers ①	hoogtelandje + bosje
	②	ruige oever (ruigte)
Chemisch	pH	7,4
	hardheid	~~[illegible]~~ 25 °d (gesamt hardte)
Biologisch	oeverbegroeiing:	brandnetels, gras, fluiteknid,
		Ovale poelslak
		Bromblaashoorn
		Platte schijfhoorn
		Zoetwater pissebed (Asellus aquatricus)
		Vlokreeft
		Waterscorpioen
		Bootsmannetje
		Sigara fallen
		Schaatsenrijder
		Schrijvertje
		Agabus didymus
		Waterkrader
		Achtoogige bloedzuiger (Erpobdella octoculata)
		Tweeoogige bloedzuiger (Helobdella stagnalis)
		Brede bloedzuiger (Glossiphonia heteroclita)
		Stekelbaarn
		Weidebeekjuffer (Calopterix splendens)
		Grote groene sabelsprinkhaan (Tettigonia viridissima)
		~~[illegible]~~
		~~[illegible]~~
		~~[illegible]~~

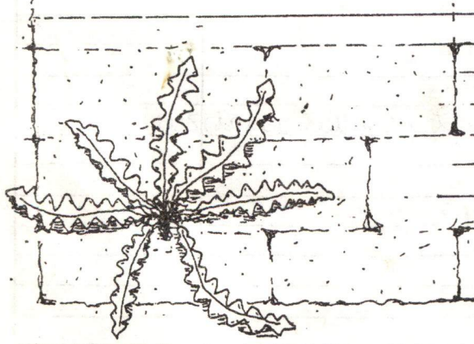

© N.J.N.- Commissie Natuurzaken '93